Instrukcja obsługi programu Tiled – Gra Czołgi

Przygotowanie środowiska:

- Pobranie programu Tiled z strony https://www.mapeditor.org/
- Po otworzeniu programu wybrać opcję „Nowa Mapa”:

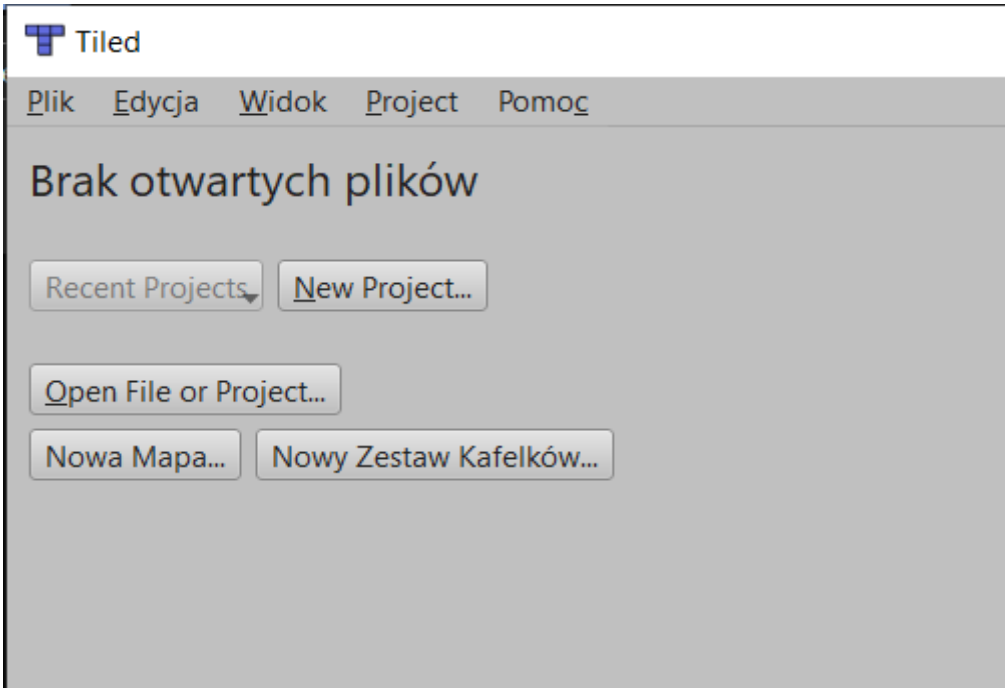

- Następnie ustawić pole Rozmiar mapy według własnych preferencji, oraz pozostałe pola tak jak na zdjęciu poniżej:

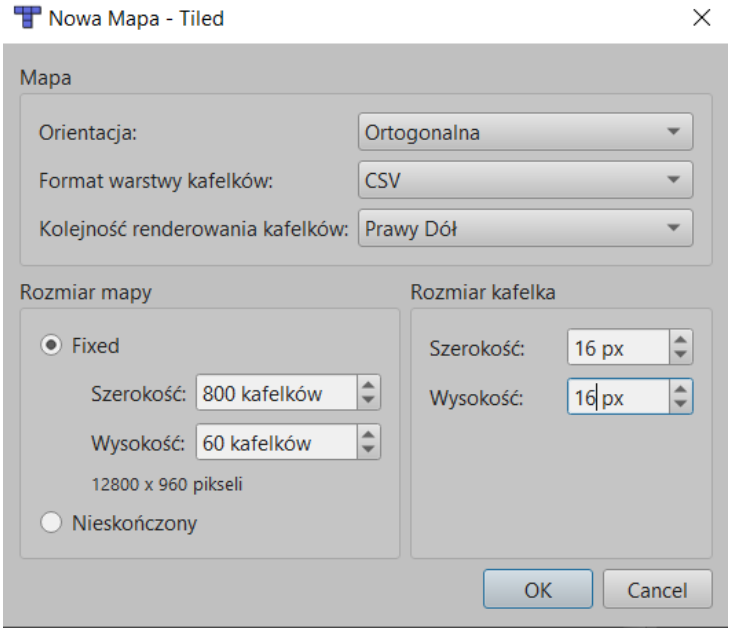

- Następnie skasować domyślną warstwę:

- 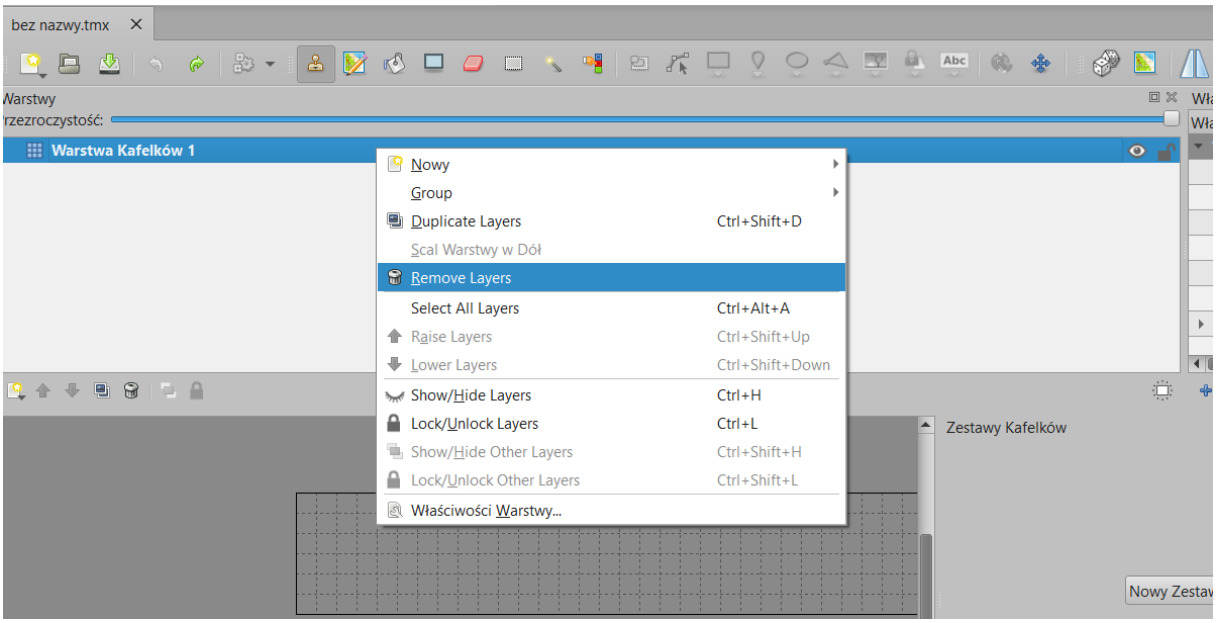

- Kolejno utworzyć dwie warstwy kafelków TOP oraz BOTTOM:

- 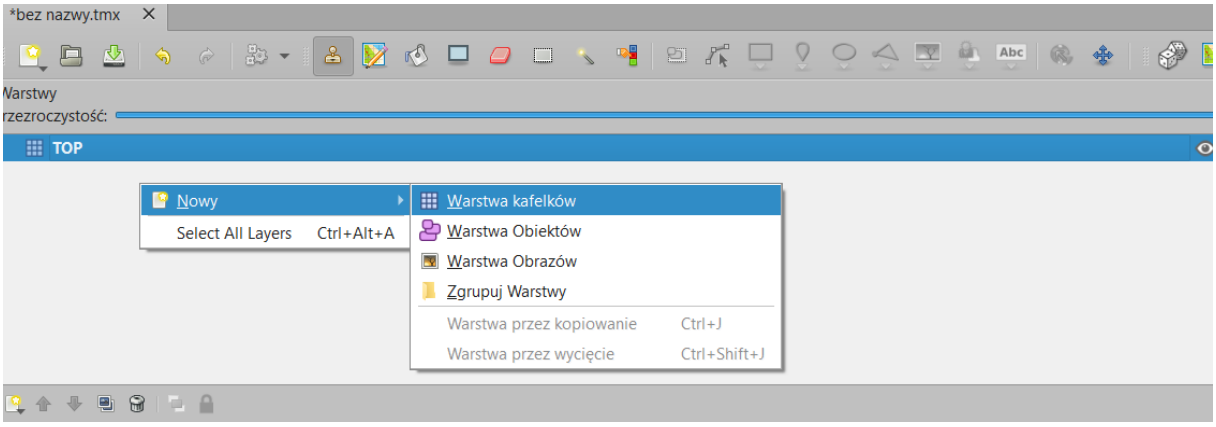

- Zaimportować wszystkie potrzebne warstwy kafelków:
  - Kliknąć na „Nowy Zestaw Kafelków”
  -

  - Następnie uzupełnić pola zgodnie z rysunkiem poniżej:

- 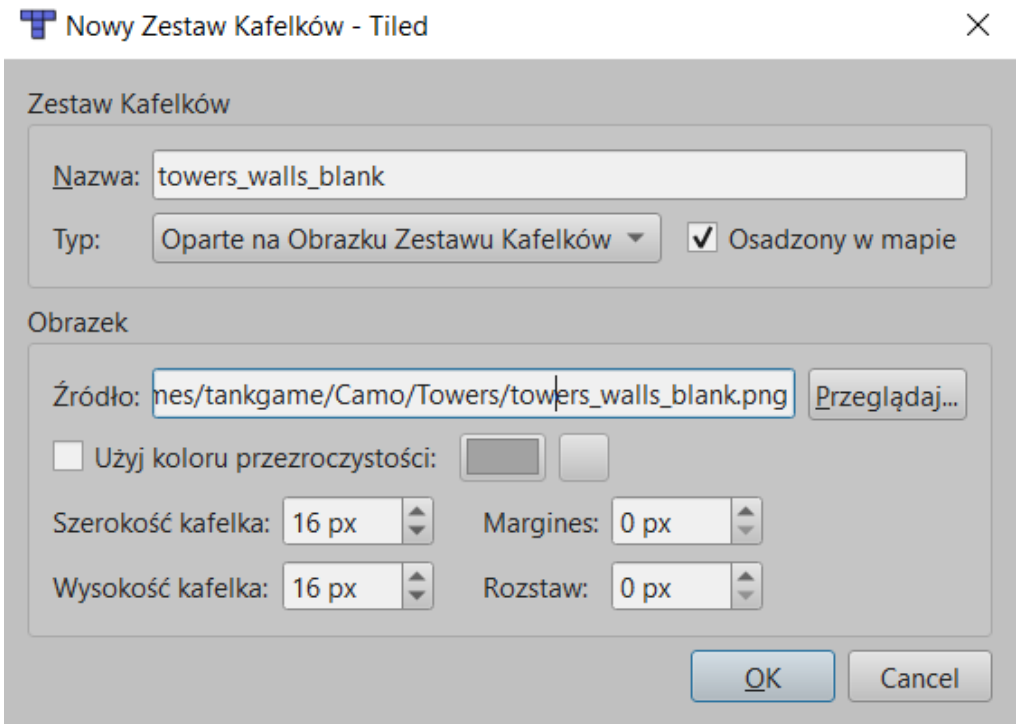

- Operacje należy powtórzyć dla assetów poniżej (tak powinna wyglądać lista po pełnym imporcie):
- 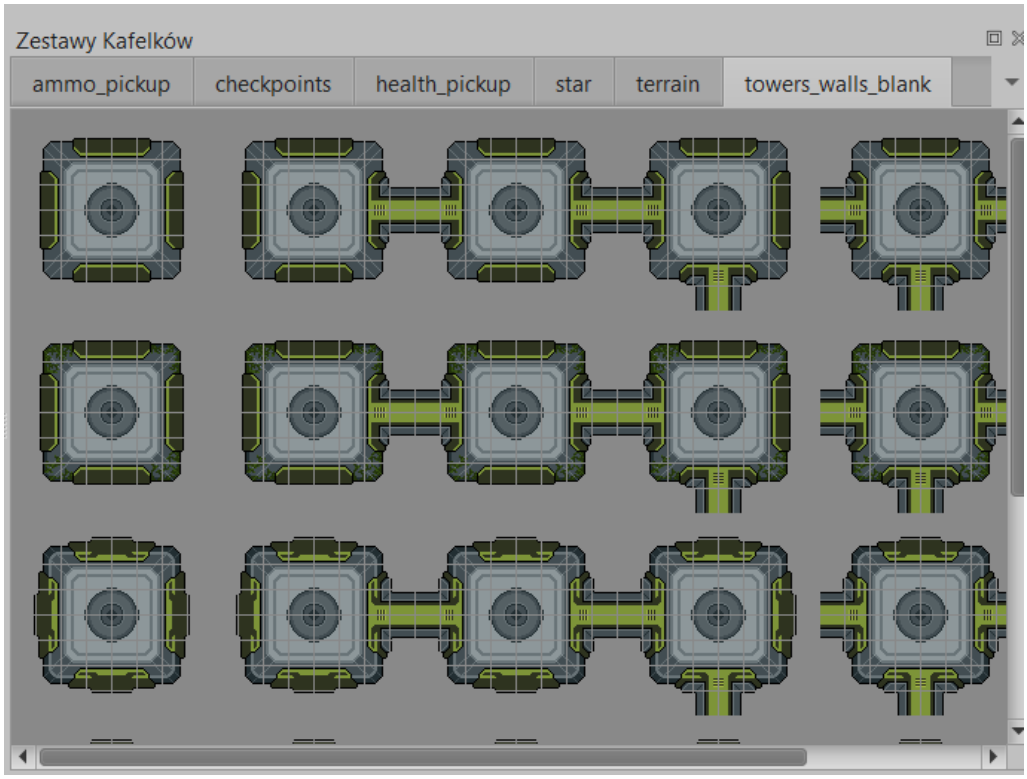

- Na każdym zestawie kafelków należy użyć opcji „Embed Tileset” (zaznaczone na czerwono na rysunku poniżej):
- 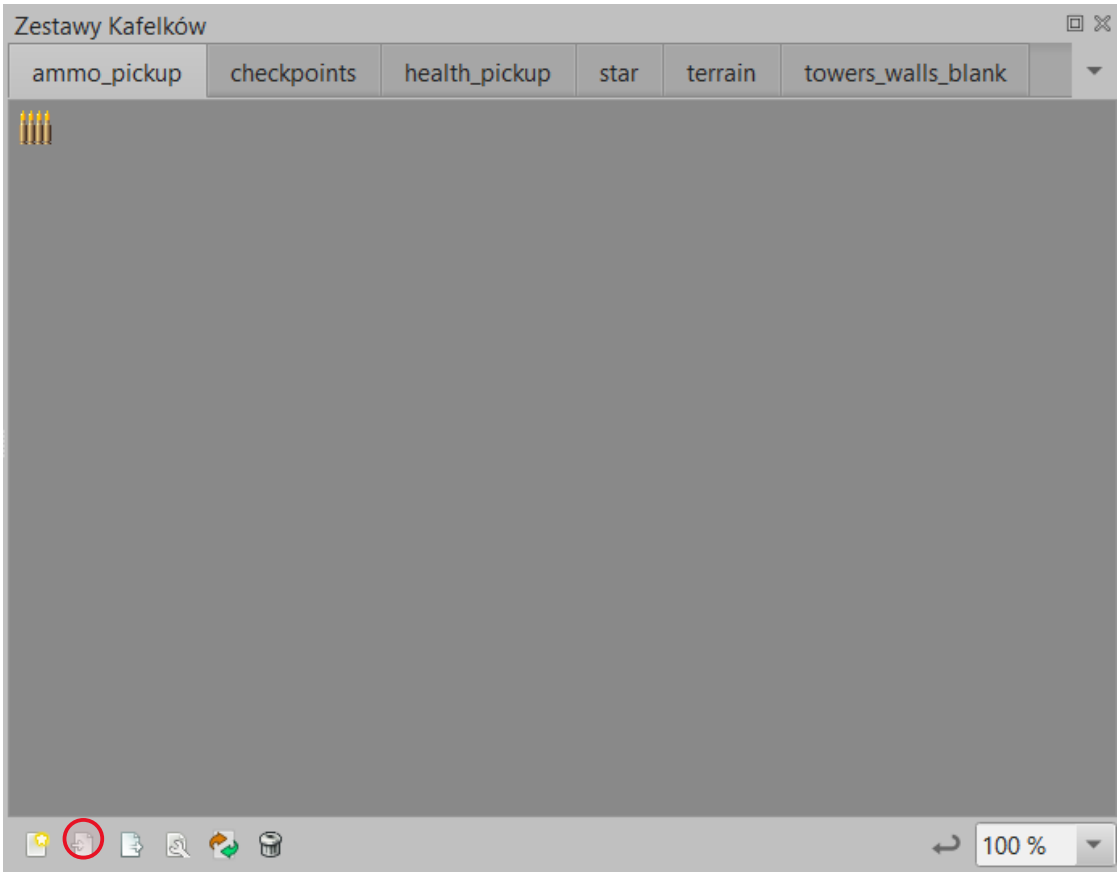

- Na zestawach kafelków trzeba ustawić właściwości typu boolean na True:
    - Dla ammo_pickup : ammo
    - Dla checkpoints : checkpoint
    - Dla health_pickup: health
    - Dla star: star

    Przykład poniżej:

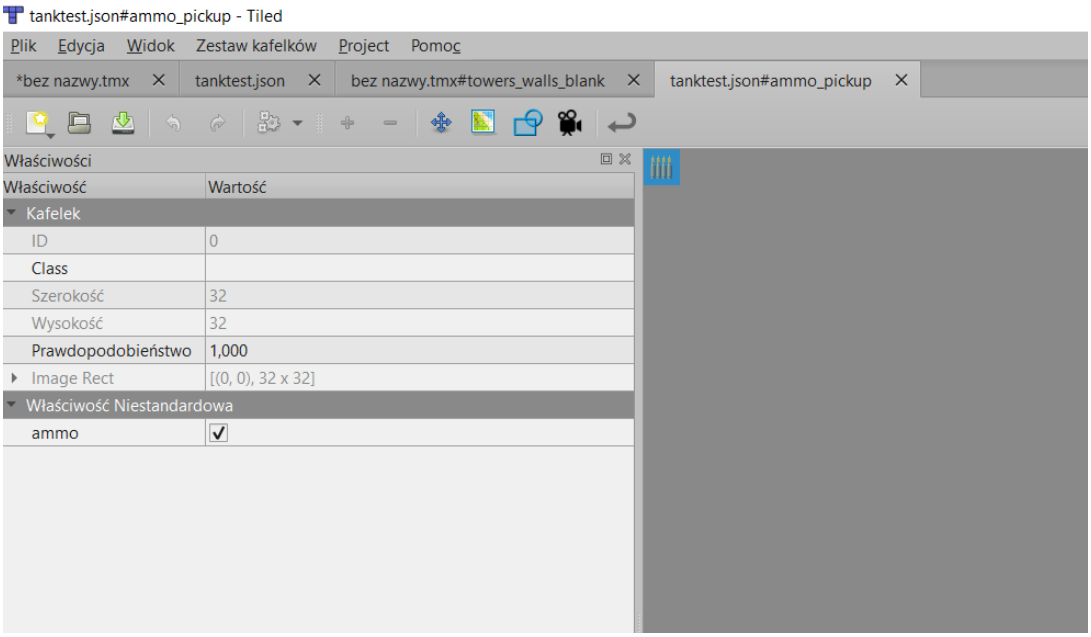

- Na zestawie kafelków tower_walls należy ustawić właściwość typu boolean collides na True (dzięki temu w grze będzie dodane kolizja dla tego kafelku) oraz pole top_left które wskazuje na lewy górny róg wieżyczki (na podstawie tego wstawiana jest strzelająca wieżyczka), przykład poniżej:
- 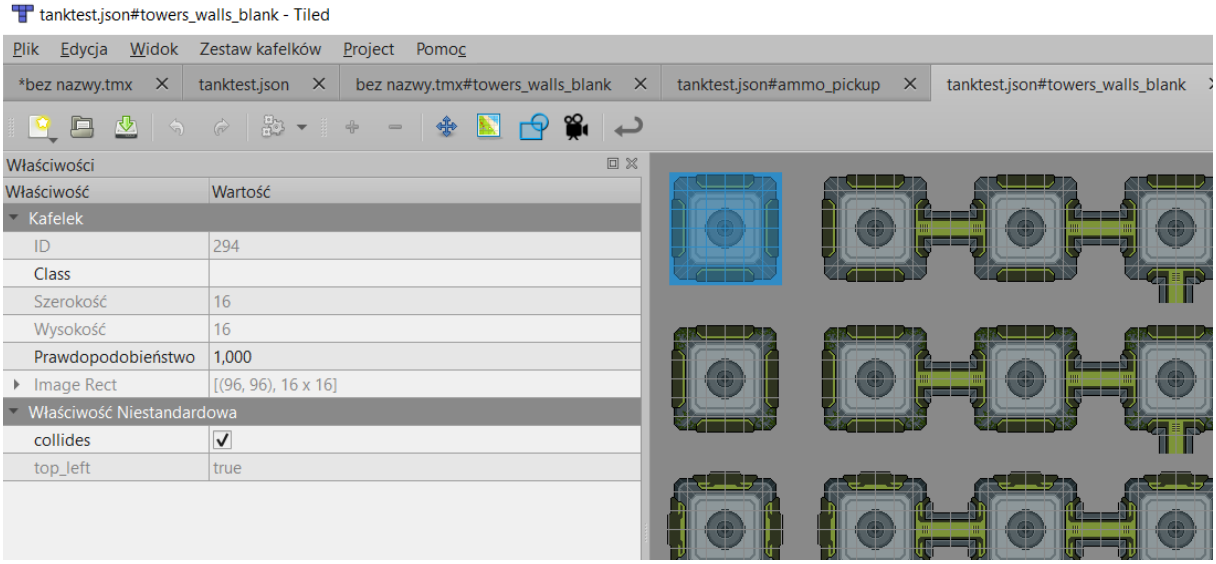

- Po tych krokach środowisko zostało przygotowane do tworzenia mapy.

Tworzenia map i ich edycja

- Na warstwie BOTTOM dodaje się tylko i wyłącznie scenerie terenu tj. tiles-y z zestawu kafelków terrain. Aby to zrobić należy zaznaczyć intersujące nas kafelki w zestawie kafelków a następnie nałożyć je na siatkę:
- 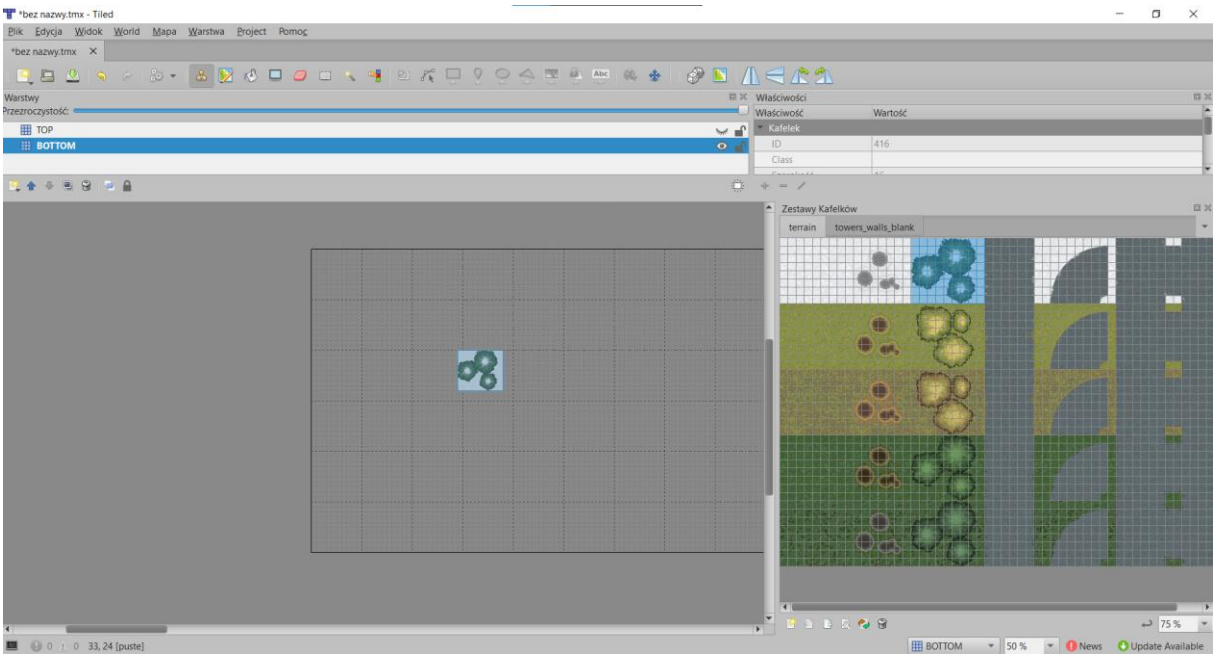

- Na warstwie TOP dodajemy pozostałe kafelki (np. wieżyczki czy pickupy), zaznaczając intersujący nas obiekt:
- 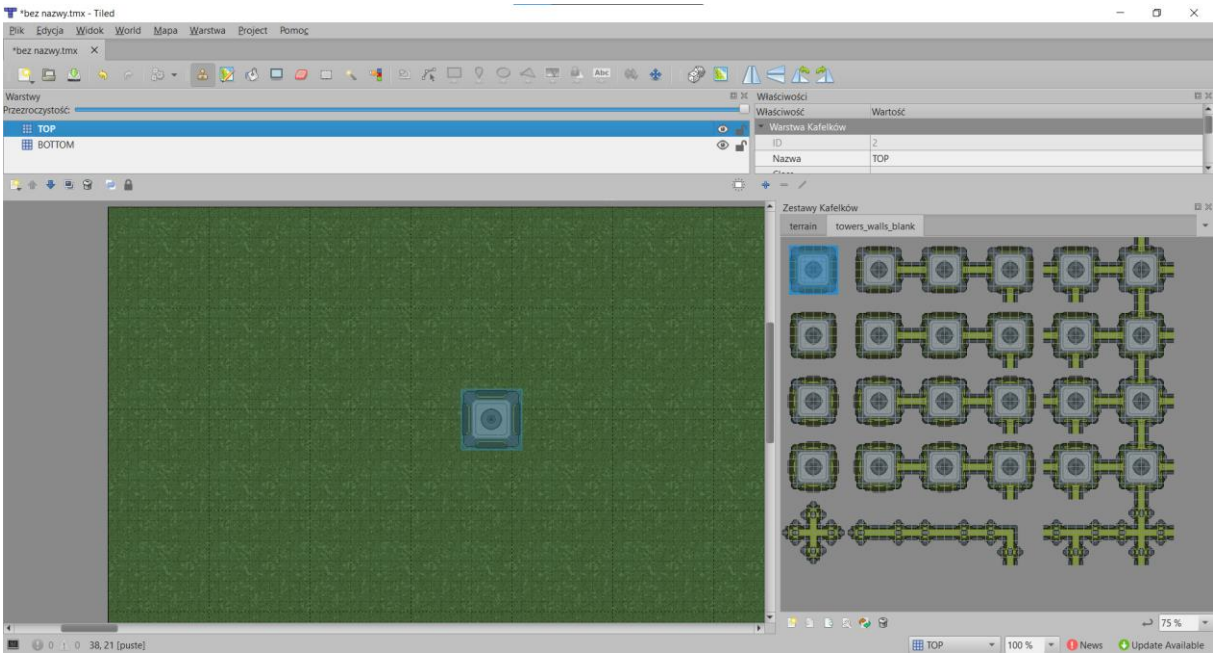

- Jeśli chcemy wstawić checkpoint (miejsce w którym zostanie wyświetlone pytanie) to należy wstawić go pomiędzy płotkami i wtedy w grze zostanie wygenerowany sensor z polem kolizji między bramkami który przy kolizji wyświetli pytanie. Należy to zrobić jak na załączonym przykładzie poniżej:
- 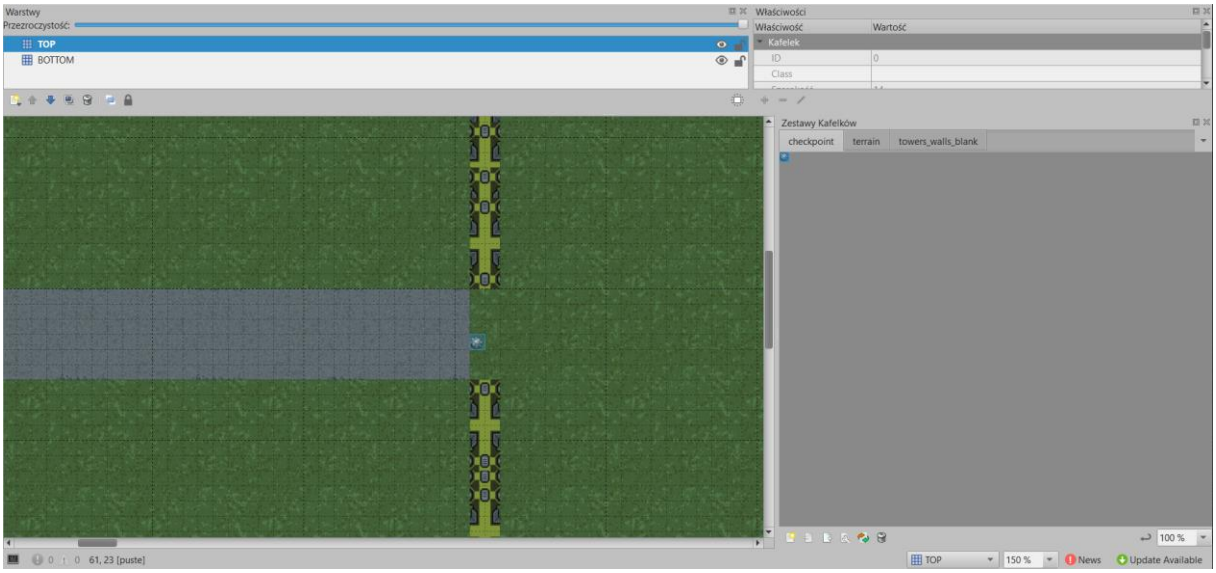

- Metą w grze, jest checkpoint który ma największe koordynaty na osi X. (ten najdalej z prawej strony mapy)

  Aby zaimportować mapę do gry, zapisujemy ją do formatu .json, a następnie wrzucamy ją do naszej aplikacji poprzez sekcję edytor map.